112) 02-19-L-B2

(1) 조사개요

산지명	북한산	시점	37°37'01.615~126°56'05.212
주소	서울시 은평구 불광동 8-286	종점	37°37'00.670~126°56'09.563

비탈면 종류	자연비탈면	구역 연장	110m
시설물 현황	도로 인접한 경사 15°의 자연비탈면, 하부 석축(H= 1.5m, L= 40m), 하부 주차장 존재		

(2) 조사결과

비탈면 경사각 (°)	비탈면 높이 (m)	종단 형상	횡단 형상	계곡 유무	계곡 연장 (m)	계곡 폭 (m)	토층 심도 (cm)	상부 외력	지하수	붕괴 이력	보호 시설	사회적 영향도	보정 점수	점수 합산 /등급
15	8	요형	상승형	무	0	0	50	전답	적음	무	양호	16	-10	26/B
3	2	3	3	1	0	0	2	2	2	1	1			

위성사진	상세위치도면
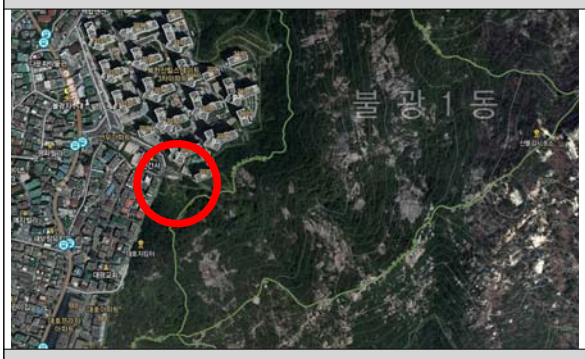	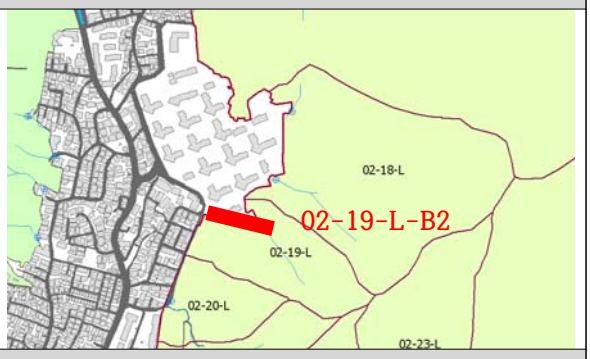
전경1	전경2
	

조사 의견	보호시설의 상태는 양호하나 우기시 비탈면에 소규모 유실이 발생할 수 있음 전반적으로 양호한 비탈면으로 피해위험성 낮음
대책 방안	현 상태 유지관리