158) 02-25-L-B1

(1) 조사개요

산지명	북한산	시점	37°36'18.126~126°56'16.436
주소	서울시 은평구 녹번동 산1	종점	37°36'25.088~126°56'14.070

비탈면 종류	자연비탈면	구역 연장	90m
시설물 현황			

(2) 조사결과

비탈면 경사각 (°)	비탈면 높이 (m)	종단 형상	횡단 형상	계곡 유무	계곡 연장 (m)	계곡 폭 (m)	토층 심도 (cm)	상부 외력	지하수	붕괴 이력	보호 시설	사회적 영향도	보정 점수	점수 합산 /등급
4	41	직선형	상승형	유	152	2	20	전, 답	완전 배수	유	양호	18	-25	37/B
1	6	2	3	5	4	4	1	2	1	6	1			

위성사진	상세위치도면
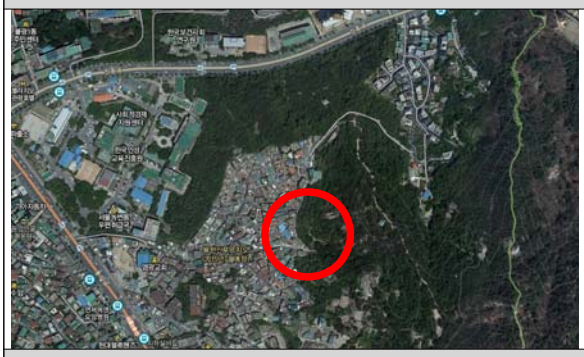	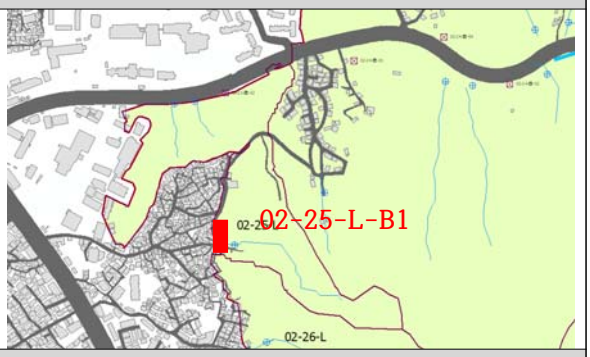
전경1	전경2
	

조사 의견	녹번 1주택 개발지 현재 공사 중 현 상황 평가 불가
대책 방안	