186) 14-21-L-01-B7

(1) 조사개요

산지명	봉산	시점	37°36'11.713~126°54'19.924
주소	서울시 은평구 역촌동 232	종점	37°36'11.042~126°54'19.623

비탈면 종류	자연비탈면	구역 연장	25 m
시설물 현황	역촌센트래빌 아파트, 경사 30°의 자연비탈면, 하부 보강토(H= 12m, L= 25m)		

(2) 조사결과

비탈면 경사각 (°)	비탈면 높이 (m)	종단 형상	횡단 형상	계곡 유무	계곡 연장 (m)	계곡 폭 (m)	토층 심도 (cm)	상부 외력	지하수	붕괴 이력	보호 시설	사회적 영향도	보정 점수	점수 합산 /등급
30	6	직선형	하강형	무	0	0	70	무	적음	무	양호	30	-10	41/C
7	2	2	1	1	0	0	3	1	2	1	1			

위성사진	상세위치도면
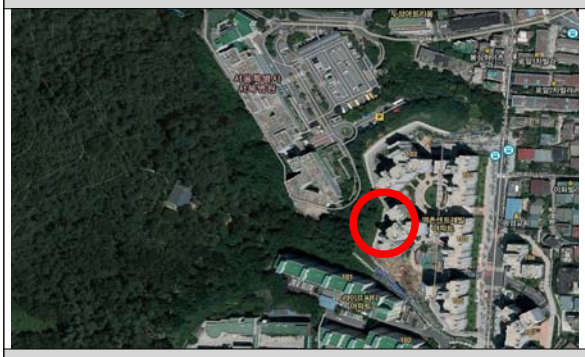	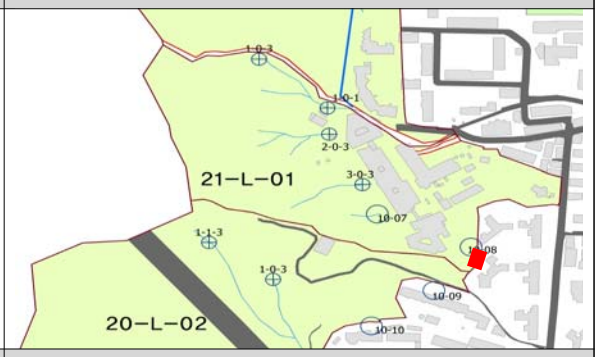
비탈면전경	하부 보강토 옹벽
	

조사 의견	식생 및 보호시설 상태 양호함. 유지관리가 양호한 비탈면으로 피해위험성이 낮음.
대책 방안	현 상태 유지관리