18) 57-03-L-B8

(1) 조사개요

산지명	불광공원	시점	37°36'57.056~126°55'48.871
주소	서울시 은평구 불광동 248	종점	37°36'59.005~126°55'42.799

비탈면 종류	자연비탈면	구역 연장	165 m
시설물 현황	라이프미성아파트 ,경사 15°의 자연비탈면, 하부 R/C 옹벽(H=7 m, L=165 m), 펜스		

(2) 조사결과

비탈면 경사각 (。)	비탈면 높이 (m)	종단 형상	횡단 형상	계곡 유무	계곡 연장 (m)	계곡 폭 (m)	토층 심도 (cm)	상부 외력	지하수	붕괴 이력	보호 시설	사회적 영향도	보정 점수	점수 합산 /등급
15	12	직선형	하강형	무	0	0	90	주택	적음	무	양호	30	-10	41/C
3	2	2	1	1	0	0	4	4	2	1	1			

위성사진	상세위치도면
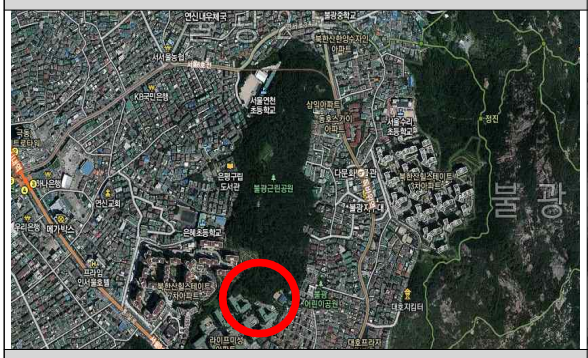	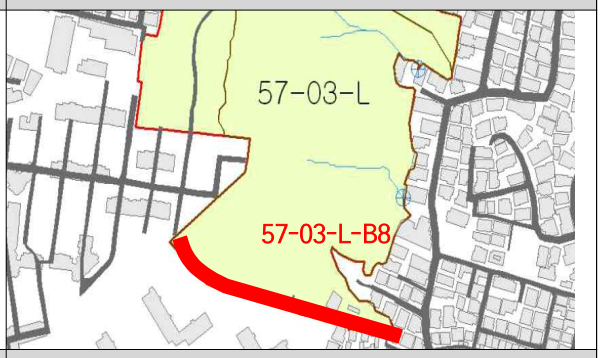

전경1	전경2
	

조사 의견	식생 양호하나 배수시설이 설치되지 않음. 보호시공이 양호한 비탈면으로 피해위험성은 낮음.
대책 방안	현 상태 유지관리