19) 59-15-L-B3

(1) 조사개요

산지명	진관공원	시점	37°38'06.174~126°55'17.489
주소	서울시 은평구 진관동 170-3	종점	37°38'05.040~126°55'19.197

비탈면 종류	자연비탈면	구역 연장	55 m
시설물 현황	숲 유치원, 경사 30°의 자연비탈면, 하부 조경석(H= 3m, L= 35m), 상부 산책로 존재		

(2) 조사결과

비탈면 경사각 (°)	비탈면 높이 (m)	종단 형상	횡단 형상	계곡 유무	계곡 연장 (m)	계곡 폭 (m)	토층 심도 (cm)	상부 외력	지하수	붕괴 이력	보호 시설	사회적 영향도	보정 점수	점수 합산 /등급
30	20	직선형	상승형	무	0	0	100	무	적음	무	양호	30	-10	46/C
7	3	2	3	1	0	0	5	1	2	1	1			

위성사진	상세위치도면
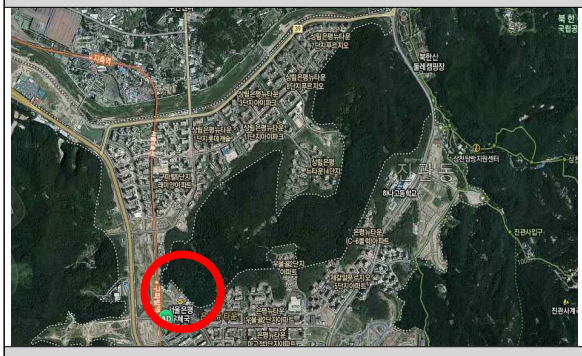	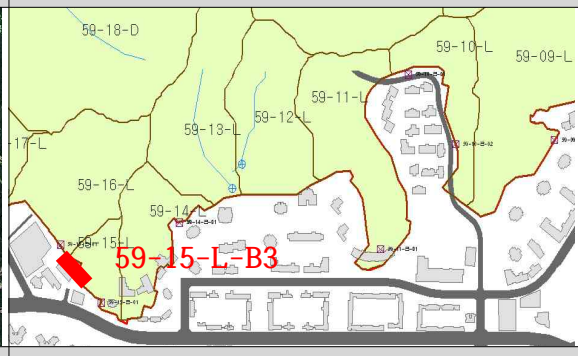

전경1	전경2
	

조사 의견	식생 및 배수시설의 상태가 양호함 전반적으로 양호한 비탈면으로 피해위험성 낮음
대책 방안	현 상태 유지관리