## 26) 60-3-L-01-B2

### (1) 조사개요

| 산지명 | 갈현공원 | 시점 | 37°37'43.034~126°55'14.269 |
|---|---|---|---|
| 주소 | 서울시 은평구 진관동 239-26 | 종점 | 37°37'44.955~126°55'14.336 |

| 비탈면 종류 | 인공비탈면 | 구역 연장 | 60 m |
|---|---|---|---|
| 시설물 현황 | 은평소방서, 경사 60°의 인공비탈면, 하부 R/C 옹벽(H= 1.5m, L= 80m), 상부 등산로 존재 | | |

### (2) 조사결과

| 비탈면 경사각 (°) | 비탈면 높이 (m) | 종단 형상 | 횡단 형상 | 절리향/ 흙강도 | 비탈면 풍화도 | 지하수 상태 | 배수 시설 | 표면 보호공상 태 | 붕괴 이력 | 비탈면 종류 | 사회적영 향도 (점수) | 보정 (점수) | 점수 합산 /등급 |
|---|---|---|---|---|---|---|---|---|---|---|---|---|---|
| 60 | 12 | 직선형 | 직선형 | 견고 | 중 | 습함 | 양호 | 양호 | 유 | 혼합 | 30 | -15 | 49/C |
| 4 | 1 | 2 | 0 | 3 | 3 | 2 | 2 | 2 | 10 | 5 | | | |

| 위성사진 | 상세위치도면 |
|---|---|
| 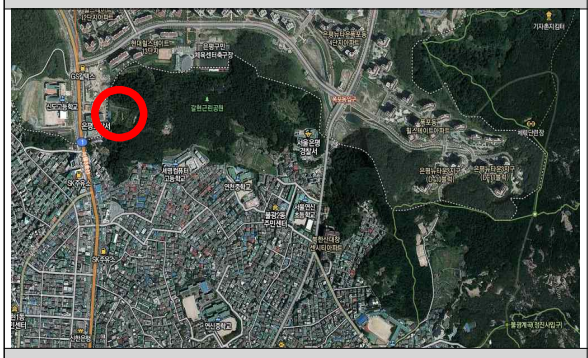 | 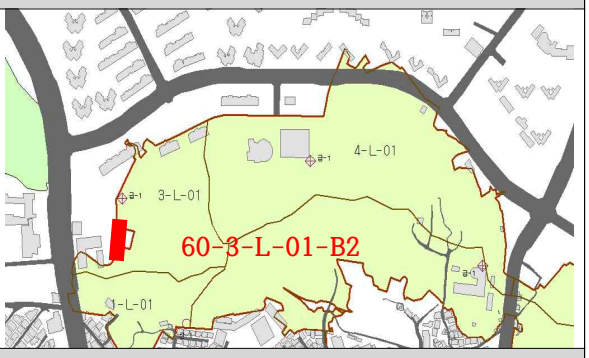  |
| 전경1 | 전경2 |
|  | |

| | |
|---|---|
| 조사 의견 | 식생 및 배수시설의 상태가 양호함.<br>보호시설의 상태는 양호하고 비탈면에 경미한 유실이 관찰되나 위험성은 낮음. |
| 대책 방안 | 유실 우려 구간의 지속적인 관찰 |