47) 60-4-L-02-B7

(1) 조사개요

산지명	갈현공원	시점	37°37'40.532~126°56'01.673
주소	서울시 은평구 진관동 산99-5	종점	37°37'37.764~126°55'58.203

비탈면 종류	자연비탈면	구역 연장	120 m
시설물 현황	폭포동 힐스테이트 아파트, 경사 25°의 자연비탈면, 하부 조경석(H= 1.5m, L= 50m), 산마루 측구		

(2) 조사결과

비탈면 경사각 (°)	비탈면 높이 (m)	종단 형상	횡단 형상	계곡 유무	계곡 연장 (m)	계곡 폭 (m)	토층 심도 (cm)	상부 외력	지하수	붕괴 이력	보호 시설	사회적 영향도	보정 점수	점수 합산 /등급
25	15	직선형	하강형	무	0	0	80	무	적음	무	양호	30	-10	40/B
5	2	2	1	1	0	0	4	1	2	1	1			

위성사진	상세위치도면
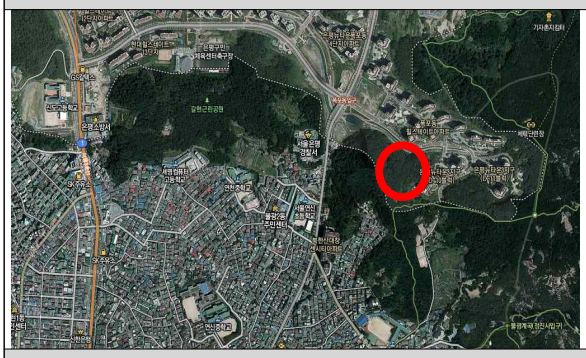	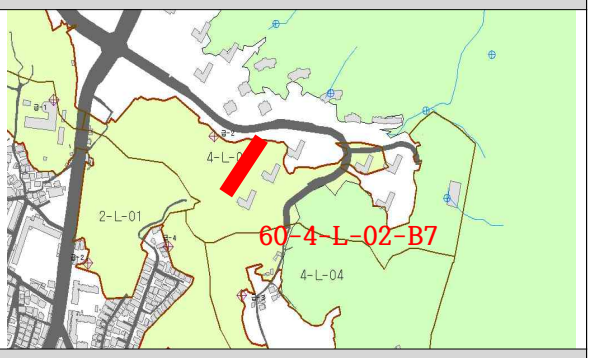
전경1	전경2
	

조사 의견	식생 및 배수시설의 상태가 양호함. 유지관리가 양호한 비탈면으로 피해위험성이 낮음.
대책 방안	현 상태 유지관리