54) 60-4-L-03-B5

(1) 조사개요

산지명	갈현공원	시점	37°37'27.977~126°55'51.282
주소	서울시 은평구 불광동 171-61	종점	37°37'29.033~126°55'50.338

비탈면 종류	자연비탈면	구역 연장	40 m
시설물 현황	현대아파트, 경사 15°의 자연비탈면, 하부 R/C 옹벽(H= 4m, L= 35m), 측구, 펜스		

(2) 조사결과

비탈면 경사각 (°)	비탈면 높이 (m)	종단 형상	횡단 형상	계곡 유무	계곡 연장 (m)	계곡 폭 (m)	토층 심도 (cm)	상부 외력	지하수	붕괴 이력	보호 시설	사회적 영향도	보정 점수	점수 합산 /등급
15	15	직선형	상승형	무	0	0	70	무	적음	무	양호	30	-10	39/B
3	2	2	3	1	0	0	3	1	2	1	1			

위성사진	상세위치도면
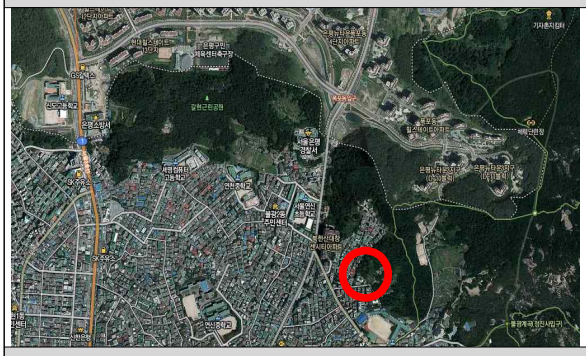	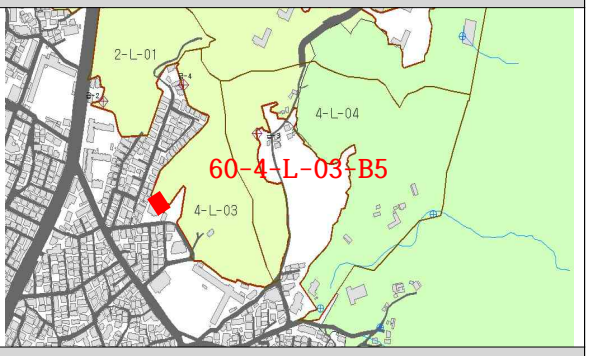
전경1	전경2
	

조사 의견	식생 및 배수시설의 상태가 양호함. 전반적으로 양호한 비탈면으로 피해위험성 낮음.
대책 방안	현 상태 유지관리