2) 유역번호 : 67-01-L-B2

(1) 조사개요

산지명	노고산공원	시점	37.554676,126.943332
주소	마포구 노고산동 20-50	종점	37.553922,126.943364

비탈면 종류	자연비탈면	구역 연장	33m
시설물 현황	배수로, 석축옹벽		

(2) 조사결과

비탈면 경사각 (°)	비탈면 높이 (m)	종단 형상	횡단 형상	계곡 유무	계곡 연장 (m)	계곡 폭 (m)	토층 심도 (cm)	상부 외력	지하수	붕괴 이력	보호 시설	사회적 영향도	보정 점수	점수 합산 /등급
30	6	요형	상승형	없음	0	0	51	무	보통	무	무	30	0	59/C
7	2	3	3	1	-	-	3	1	3	1	5			

위성사진	상세위치도면
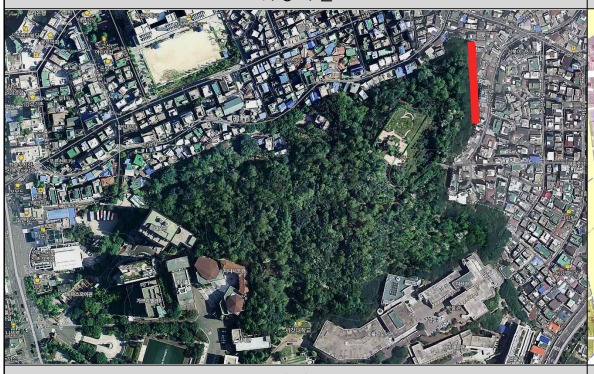	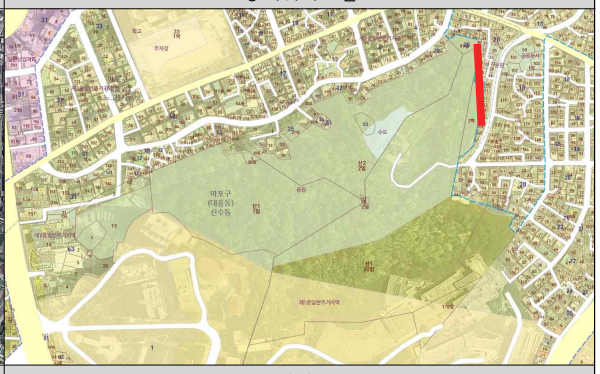
전경1	전경2
	

조사 의견	소단 및 산마루측구는 잘 정비되어 있으나 주택가 연접부의 경사가 급하며 전도수목으로 인한 피해 발생 가능
대책 방안	전도 위험 수목 제거