마포-주택-081(비탈면)

1 위치 및 시설물 종류

위 치	시 설 물
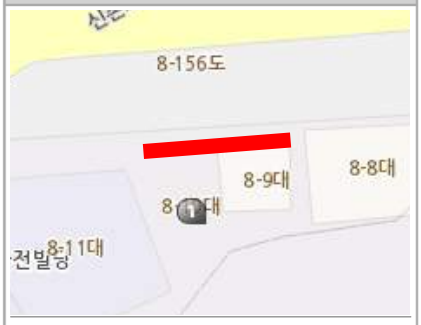	
•서울시 마포구 염리동 8-9~8-10	•비탈면(H:5.0m, L:14.5m, 방향/경사:355/80°) ► 급경사지

2 시설물 제원 및 상·하부 현황

- 해당 비탈면은 암반 비탈면으로 높이 5.0m, 연장, 14.5m 경사 80°로 구성되어 급경사지에 해당함
- 해당 비탈면의 상부에는 철거된 건물의 폐구조물이 있고, 하부에는 인도와 신촌로(8차선)가 위치함

3 시설물 상태

- 비탈면의 상단에는 높이 1.5m의 울타리가 설치되어 있고, 전면에는 셔터가 설치된 상태임
- 비탈면의 좌측 및 하부는 기반암인 편마암의 풍화암으로 이루어져 있으며, 하단 일부에는 기존 벽돌 옹벽이 있고, 이는 노후되고 심하게 파손된 상태임
- 올해 겨울(2013년)에 발생한 낙석이 다량 관찰되며, 보수 및 보강 대책이 필요할 것으로 판단됨

하단 기존 벽돌 옹벽	하부 암반	낙 석
		
•노후되고 심하게 파손된 벽돌 옹벽	•하부에 노출된 기반암	•일부 구간 적치된 낙석

4 재해위험도 평가 결과

붕 괴 위 험 성										사회적 영향도 (점수)	비탈면 종류	보정 (점수)	점수 합산 /등급
비탈면 경사각 (°)	비탈면 높이 (m)	종단 형상	횡단 형상	절리 방향	비탈면 풍화도	지하수 상태	배수시 설상태	표면시 공상태	붕괴 이력				
74 이상	5 이하	직선형	직선형	유리	하	습함	보통	불량	있음	30	암반	0	60(C)

5 종합의견

- 비탈면의 하단 일부에는 기존 벽돌 옹벽이 있고 이는 노후되고 심하게 파손된 상태이며, 전면에는 임시로 설치된 셔터가 낙석방지 시설물의 역할을 하고 있음
- 하부에 다량의 낙석이 발생해 있고 폐구조물 등 시설물의 상태가 불량한 상태로, 비탈면의 전반적인 정비와 낙석방지 시설물이 필요한 C등급으로 산정